GUÍA PARA EL REPORTE DE INFORMACIÓN DE METAS DE AGUA POTABLE Y SANEAMIENTO BÁSICO

Ministerio de Vivienda, Ciudad y Territorio

Viceministerio de Agua y Saneamiento Básico

Dirección de Política y Regulación

Bogotá, marzo de 2021

Versión 1.0

Atención al Usuario: apoyo.sinas@minvivienda.go.co

Tabla de Contenido

1 Introducción 4
2 Descripción de variables a reportar en el sistema 6
3 Insumos requeridos 7
3.1 Fuentes de información 7
3.2 Insumos técnicos 7
4 Instructivo para el reporte de la información en el sistema 8
4.1 Ingreso al sistema 8
4.2 Módulo Cargues de información 9
4.2.1 Metas Proyectadas APSB 9
4.2.1.1 Descripción y diligenciamiento de las Plantillas 10
4.2.1.2 Diligenciamiento formulario indicadores 13
4.2.1.3 Cargue de plantillas y validación de información 16
5 Procedimiento para modificar información en los Submódulos metas proyectadas APSB y/o metas ejecutadas APSB 19
6 Anexos 22
6.1 Cargue Metas Ejecutadas APSB 22
6.2 Descripción y diligenciamiento de las Plantillas 23
6.3 Diligenciamiento formulario indicadores 26
6.4 Cargue de plantillas y validación de información 29
Siglas 32

Tabla de Ilustraciones

Ilustración 1: Acceso al SINAS 8
Ilustración 2: Módulo metas proyectadas APSB 9
Ilustración 3: Plantilla total usos 10
Ilustración 4: Plantilla fuentes de financiación 11
Ilustración 5: Metas línea base APSB 12
Ilustración 6: Metas recursos APSB 13
Ilustración 7: Cargar plantillas 14
Ilustración 8: Formulario indicadores 14
Ilustración 9: Flujograma formulario indicadores 15
Ilustración 10: Cargar plantilla 16
Ilustración 11: Mensaje log de errores 17
Ilustración 12: Log de errores identificados 17
Ilustración 13: Actualizar carga 18
Ilustración 14: Mensaje de validación exitosa 18
Ilustración 15: Reporte de cargue exitoso 18
Ilustración 16: Solicitud de modificación de Información 19
Ilustración 17: Cargar archivo soporte 20
Ilustración 18: Mensaje envío de solicitud 20
Ilustración 19: Mensaje solicitud modificación de información 20
Ilustración 20: Módulo Metas Ejecutadas APSB 22
Ilustración 21: Plantilla total usos 23
Ilustración 22: Plantilla fuentes de financiación 24
Ilustración 23: Metas línea base APSB 25
Ilustración 24: Metas recursos APSB 25
Ilustración 25: Cargar plantillas 26
Ilustración 26: Formulario indicadores 27
Ilustración 27: Flujograma formulario indicadores 28
Ilustración 28: Cargar plantilla 29
Ilustración 29: Mensaje log de errores 30
Ilustración 30: Log de errores identificados 30
Ilustración 31: Actualizar carga 31
Ilustración 32: Mensaje de validación exitosa 31
Ilustración 33: Reporte de cargue exitoso 31

1 Introducción

El Decreto 028 de 2008 define la estrategia de monitoreo, seguimiento y control integral al gasto que se realice con recursos del Sistema General de Participaciones. En su artículo 17 establece que la administración municipal presentará ante el Consejo Municipal de Política Social y el Consejo Territorial de Planeación, las metas de continuidad, cobertura y calidad en la prestación de los servicios definidas en los respectivos planes sectoriales, a alcanzar anualmente y durante el respectivo período de gobierno, conforme con la política que defina el ministerio sectorial respectivo.

Frente a lo anterior, el Ministerio de Vivienda, Ciudad y Territorio (MVCT) expidió la Resolución 1067 de 2015, la cual estableció los lineamientos para la formulación de metas de cobertura, calidad y continuidad en la prestación de los servicios públicos de acueducto, alcantarillado y aseo; y se determinan los indicadores específicos y estratégicos para el desarrollo de la actividad de monitoreo al uso y ejecución de los recursos del Sistema General de Participaciones para el sector de agua potable y saneamiento básico SGP-APSB. Posterior a esto, expidió las resoluciones modificatorias 0288 de 2020 y 0098 de 2019, la primera que modificó los artículos 1° y 3° y se subroga el anexo de la Resolución 1067 del 24 de diciembre de 2015, en lo relacionado con los lineamientos para la formulación de metas de cobertura, calidad, continuidad y aseguramiento en el acceso a agua potable y saneamiento básico definidos en los planes de desarrollo municipales y distritales parael periodo 2020-2024. Mientras que la segunda, definió los indicadores específicosy estratégicos para el desarrollo de la actividad de monitoreo al uso y ejecución de los recursos del Sistema General de Participaciones para el sector de Agua Potable y Saneamiento Básico (SGP-APSB), sus ponderaciones y el nivel de riesgo.

En el anexo de la Resolución 0288 de 2020 se estableció que los municipios y distritos del país deben reportar en el Sistema de Inversiones en Agua Potable y Saneamiento Básico (SINAS)[1] las iniciativas o necesidades de proyectos de inversión, compromisos y usos, fuentes de financiación y la línea base y metas

[1] El SINAS es un sistema de acceso web a través del cual se puede consultar información asociada a los proyectos de inversiónen infraestructura del sector de agua potable y saneamiento básico ejecutados y en proceso de ejecución. Asimismo, el sistema permite hacer consultas de los principales indicadores sectoriales, de las necesidades de inversión en el sector de los municipios y distritos del país y de las condiciones de acceso a agua y saneamiento básico de su zona rural. El MVCT tiene la responsabilidad de administrar, mantener y operar este sistema de conformidad con lo establecido en el artículo 57 de la Ley1537 de 2012.

de los indicadores de cobertura, calidad, continuidad y aseguramiento en el acceso a agua potable y saneamiento básico, que debieron ser definidos en sus Planes de Desarrollo, para el periodo de gobierno 2020-2024. Por tal razón, el objetivo de la presente guía es mostrar la forma correcta de cómo se debe realizar el reporte de la información en lo referente a las Metas APSB, es decir, los compromisos y usos, fuentes de financiación, línea base, metas e indicadores.

Frente a la periodicidad del reporte de información, las metas definidas en el plan sectorial para el periodo de gobierno 2020 – 2024 deben reportarse por cada municipio a más tardar el 31 de mayo de la vigencia posterior, es decir, empezó por la vigencia 2020 el 31 de mayo de 2021 y así consecuentemente.

Por tal razón, el objetivo de la presente guía es mostrar la forma correcta de cómo se debe realizar el reporte de la información en lo referente a las Metas APSB, es decir, los compromisos y usos, fuentes de financiación, línea base y metas indicadores tanto en las metas proyectadas para para el periodo 2020-2023, así como para los avances de estas vigencias.

Para cumplir con este objetivo el presente documento está dividido principalmente en seis secciones incluyendo está breve introducción. En la segunda parte se describen las variables a reportar, mientras que en la tercera los insumos requeridos desde el punto de vista funcional y técnico para realizar el reporte de la información en el sistema. En la cuarta parte se expone el detalle del módulo desarrollado en el SINAS para que los municipios y distritos del país reporten exitosamente estas variables en el sistema[2], en la quinta se sección se describe el procedimiento para solicitar y realizar modificación de la información reportada que requiera ser actualizada. Por último, en la sección anexos se presenta el procedimiento para realizar el reporte de los avances en la ejecución de los recursos para lograr las metas planeadas.

[2] Es importante tener en cuenta que esta guía es dirigida exclusivamente a las entidades territoriales municipales.

2 Descripción de variables a reportar en el sistema

Esta sección contiene la descripción de las variables que componen el formulario y las plantillas de las metas APSB que deben registrar las entidades territoriales y distritales, para más detalles lo invitamos acceder a la ficha_metas_APSB que encontrará en la sección *Fichas de metadatos* del *Módulo de ayuda* del *Portal Web del SINAS* (o poner en el siguiente enlace).

3 Insumos requeridos

3.1 Fuentes de información

Los datos relacionados con los compromisos, usos, fuentes de financiación y recursos requeridos para llevar a cabo las inversiones establecidas, se deben obtener a partir de la información presupuestal registrada para el sector de agua potable y saneamiento básico en los planes de desarrollo municipales o distritales.

3.2 Insumos técnicos

Para acceder al SINAS es necesario que las administraciones municipales cuenten con los requerimientos que se enuncian a continuación:

- Dispositivo móvil o computador portátil o de escritorio, con acceso a Internet.
- Usuario y clave de acceso al SINAS.
- Navegador (Microsoft Edge – Mozilla Firefox – Safari – Chrome).

Si no se tiene el usuario y contraseña para acceder al sistema, se puede solicitar a través del correo apoyo.sinas@minvivienda.gov.co desde un correo institucional de la administración municipal.

4 Instructivo para el reporte de la información en el sistema

4.1 Ingreso al sistema

El ingreso al SINAS se realiza accediendo en su navegador ya sea desde un dispositivo móvil o de una computadora con la siguiente dirección URL:

sinas.minvivienda.gov.co

Allí se visualiza la página de autenticación donde se debe digitar el usuario y contraseña asignado y luego dar clic en el botón ingresar (*ver ilustración 1*).

Ilustración 1: Acceso al SINAS

Una vez acceda con su usuario y contraseña válidos, ingresará a la pantalla principal del sistema SINAS, donde según los perfiles que tenga asociados, podrá ingresar al módulo que se detallan a continuación.

4.2 Módulo Cargues de información

4.2.1 Metas Proyectadas APSB

Este módulo captura la información asociada a los recursos requeridos para llevar a cabo las inversiones planeadas, sus posibles fuentes de financiación y demás compromisos y usos que haya identificado la administración municipal para el periodo de gobierno en el sector de APSB. Adicionalmente, se debe registrar la información de la línea bases y las metas de los indicadoresde cobertura, calidad, continuidad y aseguramiento en el acceso a agua potable y saneamientobásico.

Para acceder a la herramienta que le permitirá reportar está información, diríjase al módulo **Cargues de información** e ingrese por la opción **Metas Proyectadas APSB** y luego dar clic en la opción **Registrar** (*ver ilustración 2*).

Ilustración 2: Módulo metas proyectadas APSB

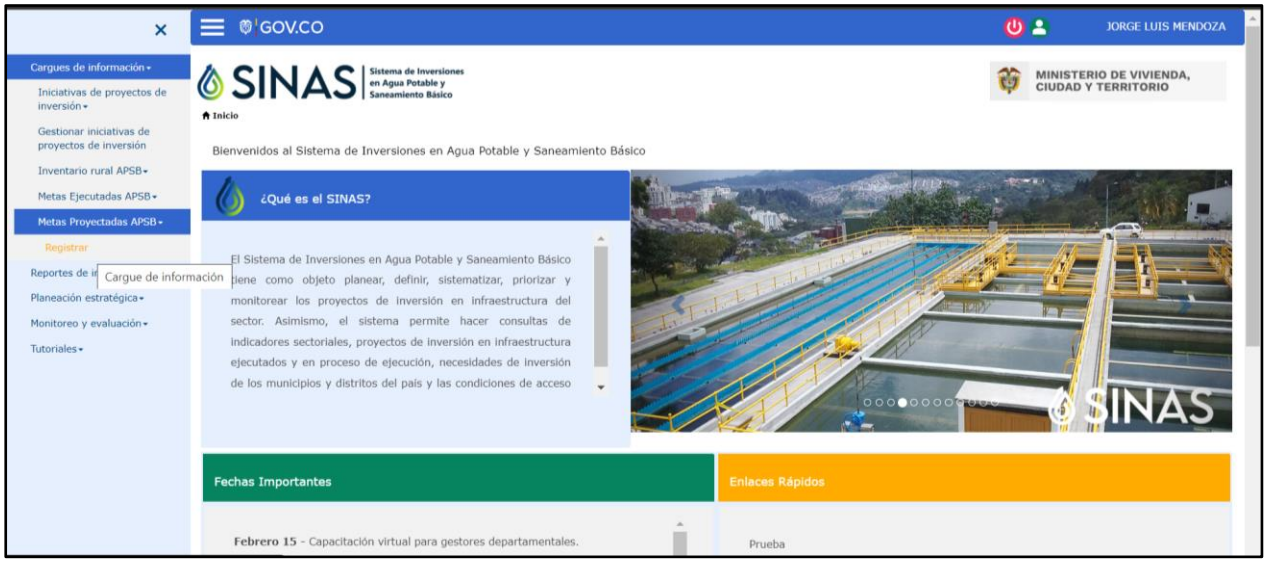

Una vez ingrese al módulo debe descargar para su diligenciamiento la plantilla base que se encuentra en formato Excel, dando clic en el botón “Generar Plantilla” ubicado en el panel lateral derecho del cuadrante medio de la pantalla. El archivo Excel descargado está compuesto por cuatro hojas de cálculo denominados de la siguiente forma:

- Plantilla Total Usos.
- Plantilla Fuentes.

- Plantilla Metas Línea Base APSB.
- Plantilla Metas Recursos APSB.

4.2.1.1 Descripción y diligenciamiento de las Plantillas

Una vez descargado el archivo se debe diligenciar los campos correspondientes a cada plantilla sin manipular información fuera de ella[3] y teniendo en cuenta las siguientes instrucciones:

4.2.1.1.1 Plantilla Total Usos

En la columna A se encuentra precargado el listado de los Compromisos y Usos (*ver ilustración 3*). En las columnas B, C, D y E aparecen las vigencias correspondientes al periodo de la administración Año 1, Año 2, Año 3 y Año 4, respectivamente, en las cuales se debe ingresar el valor de los recursos asignados a cada compromiso o uso. Luego debe seleccionar de las listas desplegables en las celdas de las columnas F, G y H, la fuente de financiación correspondiente. Sólo si el compromiso o uso tiene más de una fuente de financiación puede hacer uso de las columnas G y H correspondientes a "Fuente de Financiación 2" y "Fuente de Financiación 3".

Ilustración 3: Plantilla total usos

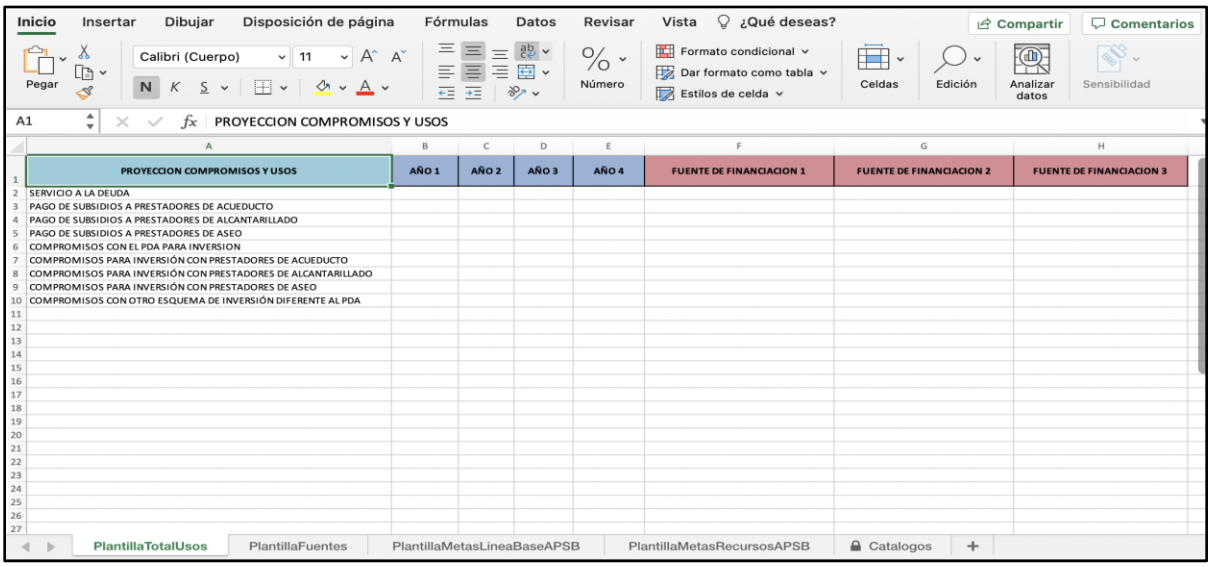

[3] No modifique los textos que ya vienen prediligenciados en las plantillas, ni elimine o adicione filas y columnas de las mismas.

4.2.1.1.2 Plantilla Fuentes

En la columna A se encuentra precargados el listado de las fuentes de financiación (*ver ilustración 4).* En las columnas B, C, D y E aparecen las vigencias correspondientes al periodo de la administración Año 1, Año 2, Año 3 y Año 4, respectivamente, en las cuales se debe ingresar el valor de los recursos de cada fuente de financiación a registrar. Para la correcta validación de esta plantilla es obligatorio registrar al menos la fuente de financiación del primer año.

Ilustración 4: Plantilla fuentes de financiación

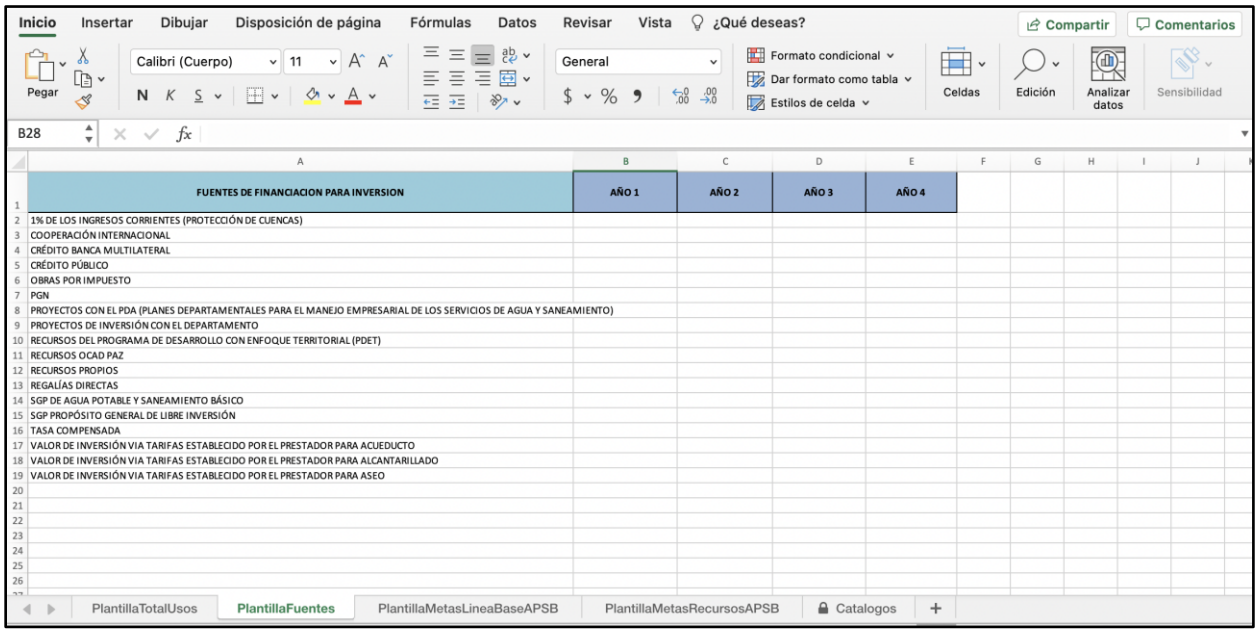

FUENTES DE FINANCIACION PARA INVERSION	AÑO 1	AÑO 2	AÑO 3	AÑO 4
1% DE LOS INGRESOS CORRIENTES (PROTECCIÓN DE CUENCAS)				
COOPERACIÓN INTERNACIONAL				
CRÉDITO BANCA MULTILATERAL				
CRÉDITO PÚBLICO				
OBRAS POR IMPUESTO				
PGN				
PROYECTOS CON EL PDA (PLANES DEPARTAMENTALES PARA EL MANEJO EMPRESARIAL DE LOS SERVICIOS DE AGUA Y SANEAMIENTO)				
PROYECTOS DE INVERSIÓN CON EL DEPARTAMENTO				
RECURSOS DEL PROGRAMA DE DESARROLLO CON ENFOQUE TERRITORIAL (PDET)				
RECURSOS OCAD PAZ				
RECURSOS PROPIOS				
REGALÍAS DIRECTAS				
SGP DE AGUA POTABLE Y SANEAMIENTO BÁSICO				
SGP PROPÓSITO GENERAL DE LIBRE INVERSIÓN				
TASA COMPENSADA				
VALOR DE INVERSIÓN VIA TARIFAS ESTABLECIDO POR EL PRESTADOR PARA ACUEDUCTO				
VALOR DE INVERSIÓN VIA TARIFAS ESTABLECIDO POR EL PRESTADOR PARA ALCANTARILLADO				
VALOR DE INVERSIÓN VIA TARIFAS ESTABLECIDO POR EL PRESTADOR PARA ASEO				

4.2.1.1.3 Plantilla Metas Línea Base APSB

Diligencie la Plantilla Metas Línea Base APSB, ingresando en las celdas de las columnas B a la S , el valor de la línea base y las metas para el Año 1, Año 2, Año 3, Año 4 en cada uno de los indicadores (*ver ilustración 5*).

El valor para cada vigencia no debe ser inferior al valor registrado en la Línea Base ni superior al 100%. Adicionalmente, la meta se debe registrar de manera acumulada, teniendo en cuenta que el valor de cada periodo debe ser mayor que el del año anterior, por ejemplo:

Línea Base	0,5
Año 1	0,6
Año 2	0,7
Año 3	0,8
Año 4	0,9

Tener en cuenta que los valores a registrar en las columnas L y O, correspondiente a los indicadores Toneladas Urbanas Dispuestas Sitio de Disposición Final e Índice de Pérdidas por Suscriptor Facturado en la Zona Urbana respectivamente, deben ser diligenciados con números enteros mayor que cero. Para el resto de los indicadores de esta plantilla se deben reportar en valores porcentuales entre 0 y 1, utilizando como separador decimal la coma (,).

Ilustración 5: Metas línea base APSB

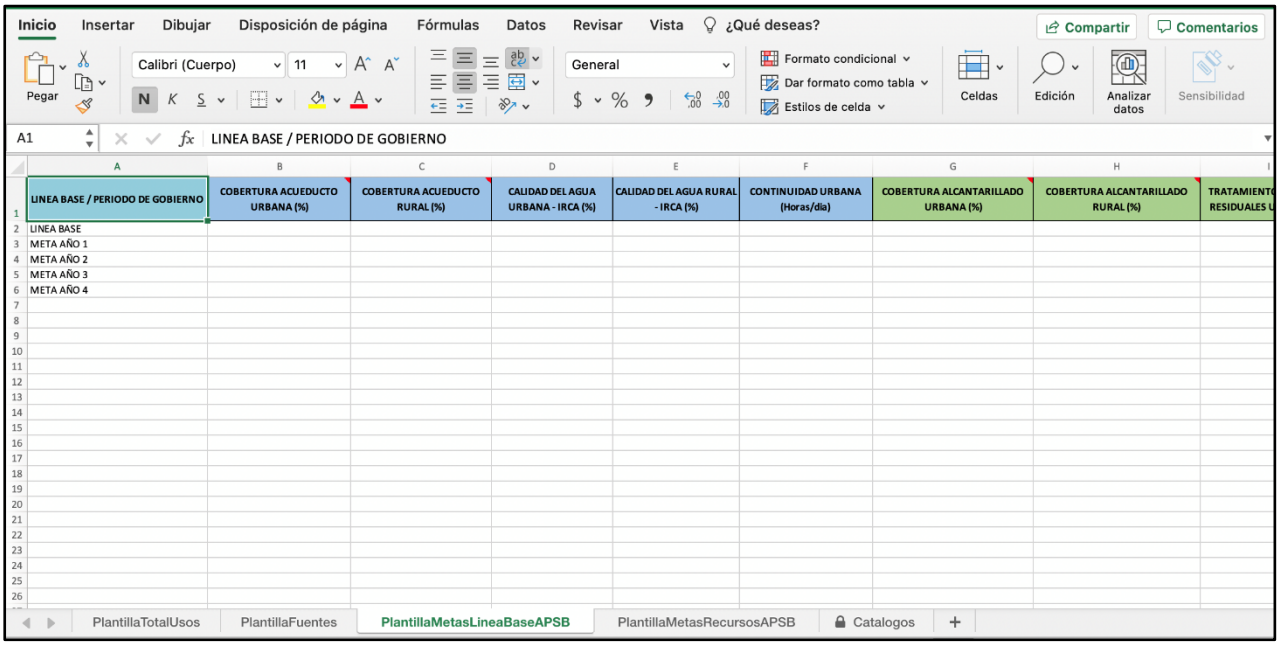

4.2.1.1.4 Plantilla Metas Recursos APSB

Diligencie la Plantilla Metas Recursos APSB, ingresando en la celda de la columna C el monto de los Recursos a Invertir para cumplir con las metas de los indicadores descritos en la columna B (*ver ilustración 6*).

Ilustración 6: Metas recursos APSB

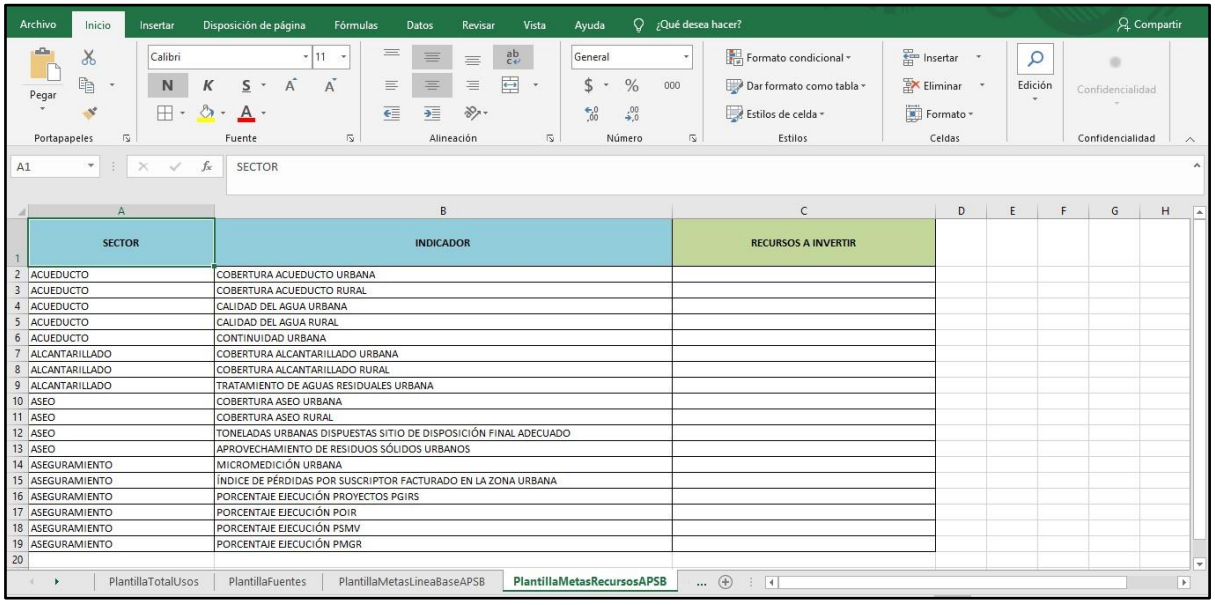

SECTOR	INDICADOR	RECURSOS A INVERTIR
ACUEDUCTO	COBERTURA ACUEDUCTO URBANA	
ACUEDUCTO	COBERTURA ACUEDUCTO RURAL	
ACUEDUCTO	CALIDAD DEL AGUA URBANA	
ACUEDUCTO	CALIDAD DEL AGUA RURAL	
ACUEDUCTO	CONTINUIDAD URBANA	
ALCANTARILLADO	COBERTURA ALCANTARILLADO URBANA	
ALCANTARILLADO	COBERTURA ALCANTARILLADO RURAL	
ALCANTARILLADO	TRATAMIENTO DE AGUAS RESIDUALES URBANA	
ASEO	COBERTURA ASEO URBANA	
ASEO	COBERTURA ASEO RURAL	
ASEO	TONELADAS URBANAS DISPUESTAS SITIO DE DISPOSICIÓN FINAL ADECUADO	
ASEO	APROVECHAMIENTO DE RESIDUOS SÓLIDOS URBANOS	
ASEGURAMIENTO	MICROMEDICIÓN URBANA	
ASEGURAMIENTO	ÍNDICE DE PÉRDIDAS POR SUSCRIPTOR FACTURADO EN LA ZONA URBANA	
ASEGURAMIENTO	PORCENTAJE EJECUCIÓN PROYECTOS PGIRS	
ASEGURAMIENTO	PORCENTAJE EJECUCIÓN POIR	
ASEGURAMIENTO	PORCENTAJE EJECUCIÓN PSMV	
ASEGURAMIENTO	PORCENTAJE EJECUCIÓN PMGR	

4.2.1.2 Diligenciamiento formulario indicadores

Una vez diligenciada la información de las plantillas descargada se procede a cargar dicha información, para esto debe dar clic en el botón "Cargar plantilla" que se encuentra en el panel lateral derecho, cuadrante medio del mismo (*ver ilustración 7*).

Ilustración 7: Cargar plantillas

Una vez se da clic en el botón se mostrará el formulario de información referente a los Indicadores cualitativos (*ver ilustración 8*): Tratamiento de Residuos Sólidos Urbanos, Disposición de Residuos Sólidos y Gobierno Corporativo.

Ilustración 8: Formulario indicadores

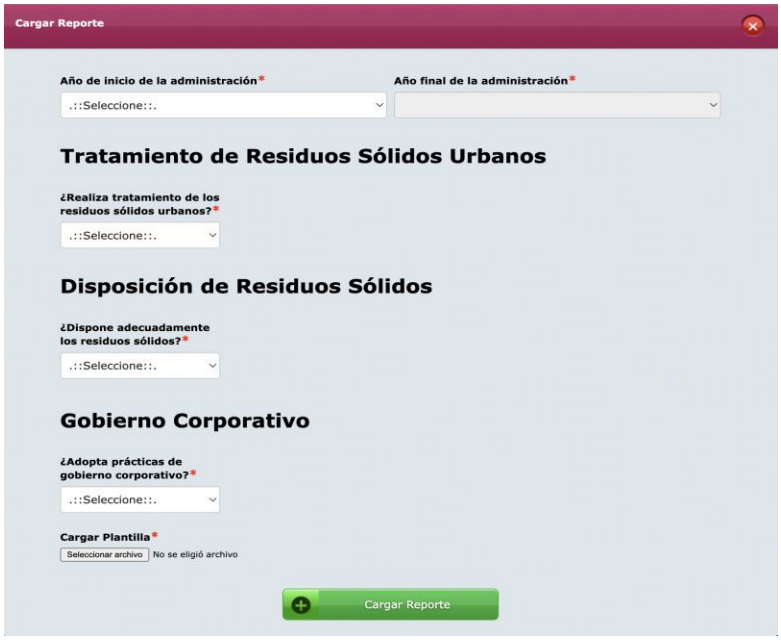

A continuación (*ver ilustración 9*), se describe la forma correcta de diligenciar este formulario:

Ilustración 9: Flujograma formulario indicadores

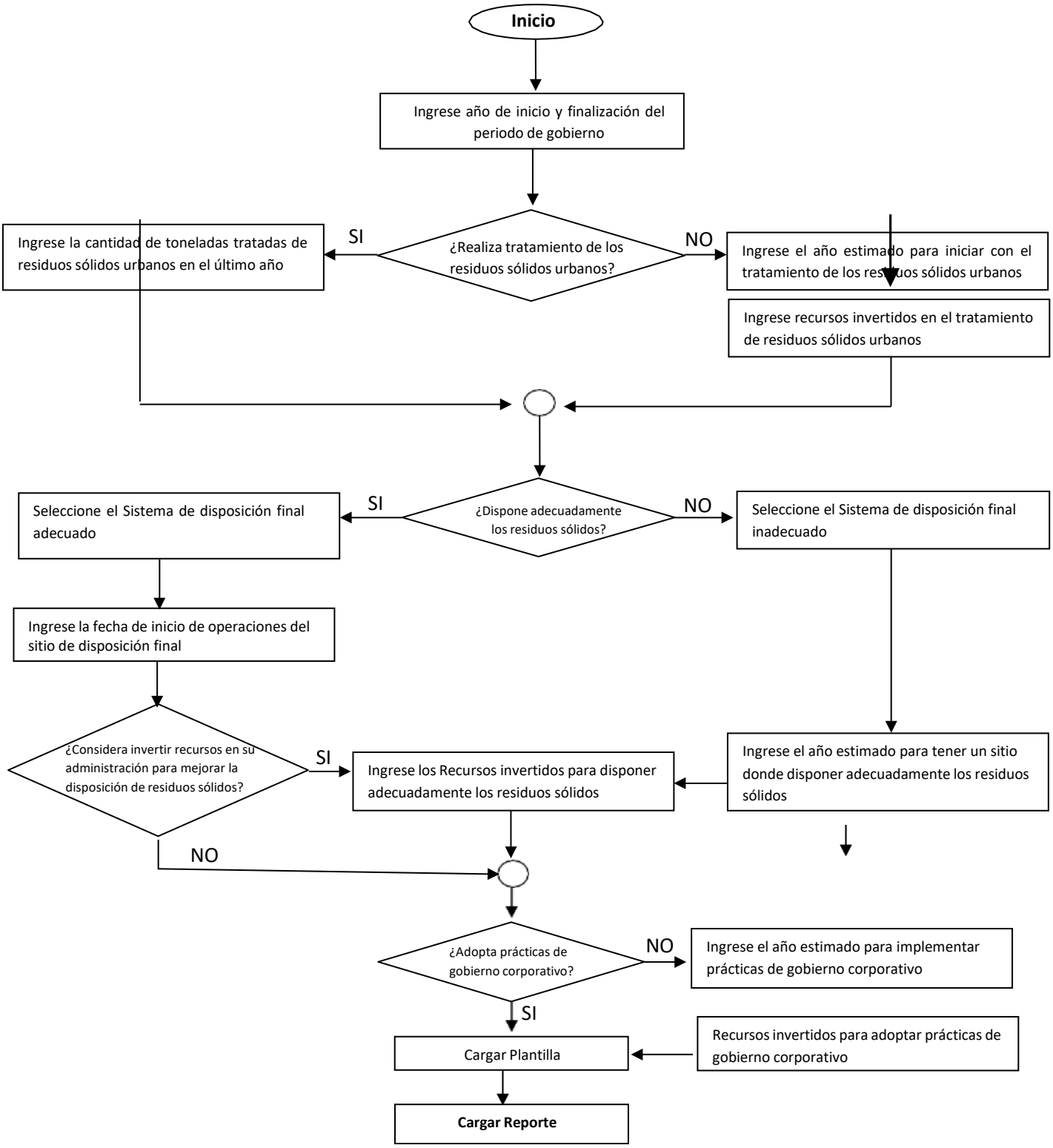

4.2.1.3 Cargue de plantillas y validación de información

Como se observa en la *ilustración 9*, una vez se diligencia el formulario de indicadores se debe proceder a cargar en el sistema el archivo en formato Excel que contiene las plantillas. Para ello se debe dar clic en el botón "Cargar Plantilla" (*ver ilustración 10*).

Ilustración 10: Cargar plantilla

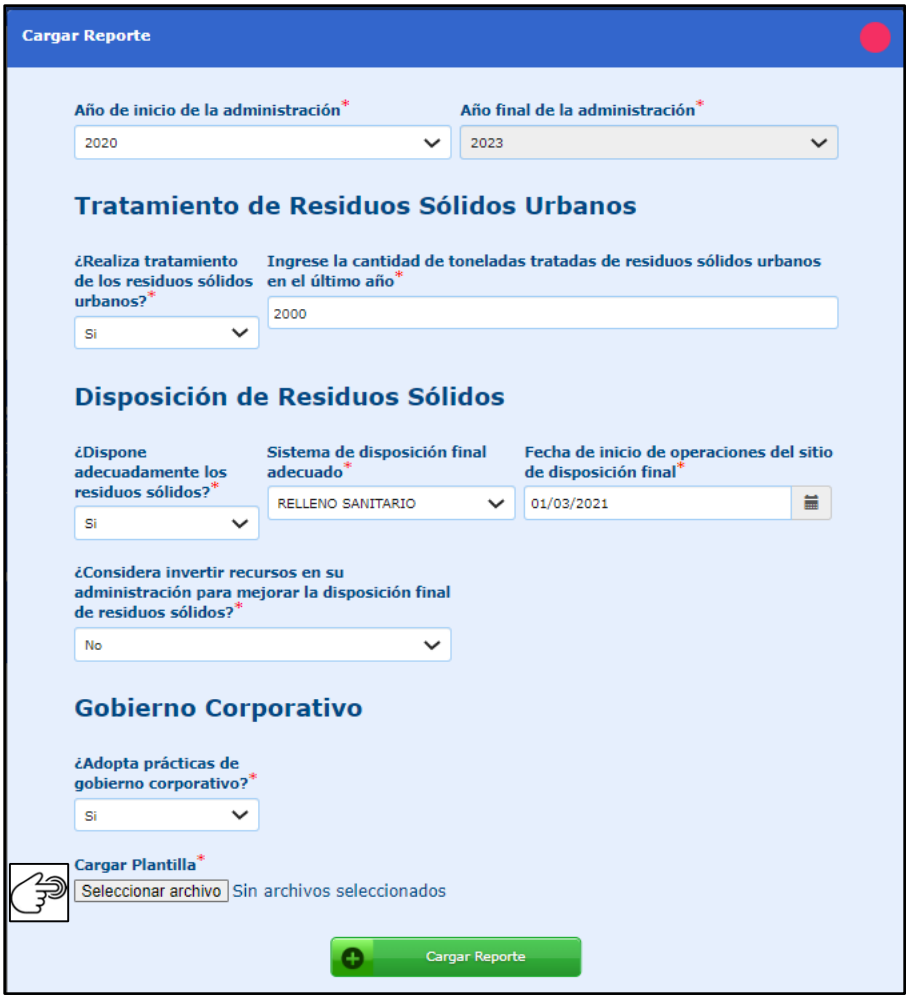

Una vez se dé clic en el botón cargar reporte, el sistema realiza las validaciones correspondientes al archivo antes de realizar la carga de la información. Si el sistema detecta errores mostrará un mensaje informando que no fue posible el cargue de la información, ya que el archivo que se intenta cargar presenta inconsistencias, este mensaje habilita un enlace para la visualización del Log de errores (*ver ilustración 11*).

Ilustración 11: Mensaje log de errores

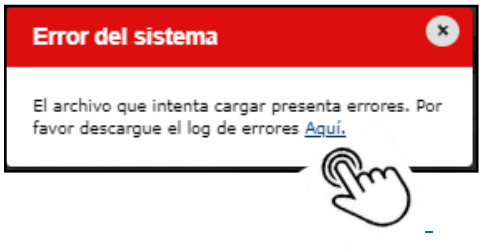

Los errores detectados en el archivo serán identificados fácilmente, ya que la celda se pondrá de color amarillo y esta tendrá un comentario el cual informará la procedencia del error (*ver ilustración 12).*

Ilustración 12: Log de errores identificados

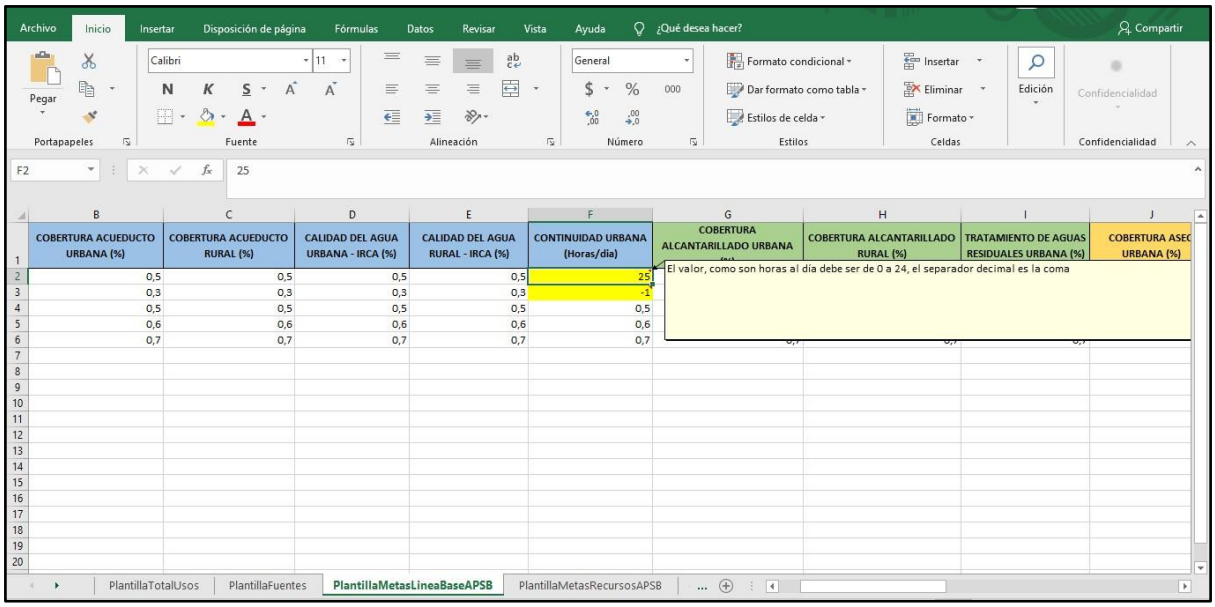

Una vez se corrijan los errores debe proceder a cargar de nuevo el archivo utilizando para ello el icono del lápiz que indica "Actualizar Carga" (*ver ilustración 13*).

Ilustración 13: Actualizar carga

Si el archivo supera las validaciones realizadas por el sistema, se mostrará un mensaje informando que la carga se procesó y se realizó exitosamente, habilitando un enlace para visualizar y descargar el certificado del reporte exitoso (*ver ilustraciones 14 y 15).*

Ilustración 14: Mensaje de validación exitosa

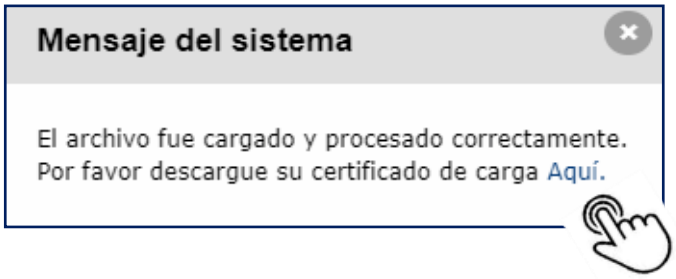

Ilustración 15: Reporte de cargue exitoso

5 Procedimiento para modificar información en los Submódulos metas proyectadas APSB y/o metas ejecutadas APSB

El ente territorial podrá solicitar la modificación de la información que reportó de su municipio en el **Módulo Cargues de información** teniendo en cuenta los siguientes pasos:

a. Diríjase al **submódulo Metas Proyectadas APSB,** haga clic en **Registrar** y a continuación en el botón del archivo para la vigencia que se quiere modificar y que se encuentra en el panel lateral izquierdo del cuadrante medio de la pantalla (*ver ilustración 16).*

Ilustración 16: Solicitud de modificación de Información

b. Al dar clic en el botón del lápiz se abrirá una ventana donde debe proceder a adjuntar el archivo soporte para realizar la solicitud modificación de información (*ver ilustración 17*). Antes de dar clic en el botón "Solicitar modificación de información" cerciórese que el documento soporte contenga la debida justificación de la solicitud y que se encuentre firmado por el representante legal del municipio.

Ilustración 17: Cargar archivo soporte

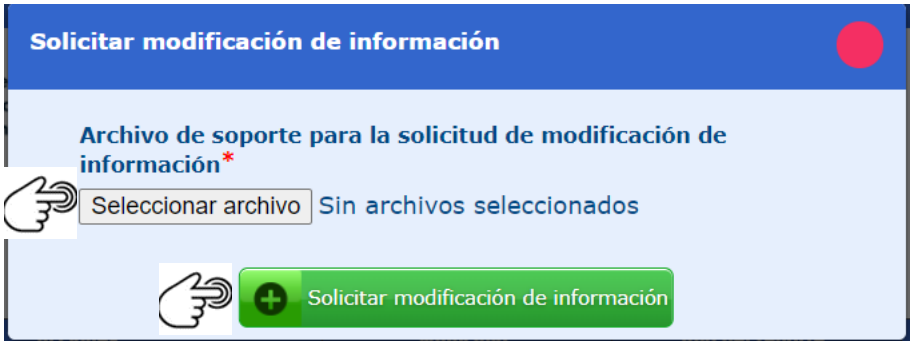

Una vez solicitada la modificación de información, el sistema mostrará un mensaje informando que se ha enviado la solicitud de modificación de información (*ver ilustración 18*) y, a su vez, el estado de la información en el sistema pasará de **"Reporte exitoso"** a **"Solicitud de Modificación de Información**" (*ver ilustración 19*).

Ilustración 18: Mensaje envío de solicitud

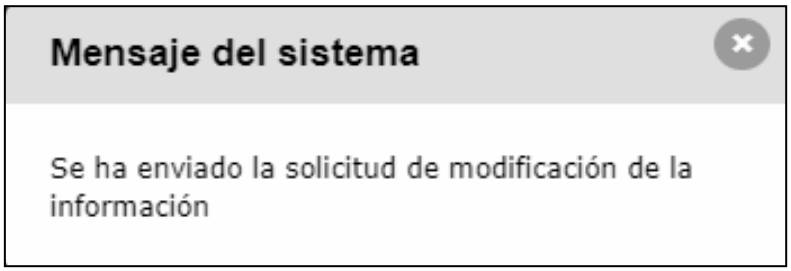

Ilustración 19: Mensaje solicitud modificación de información

c. La solicitud de modificación registrada en el sistema será revisada por el equipo de soporte funcional del SINAS y en caso de cumplir con los parámetros establecidos se procederá a autorizar la misma. Una vez autorizada la modificaciónde la información el usuario de la entidad territorial podrá eliminar el reporte y realizar de nuevo el cargue de información.

6 Anexos

6.1 Cargue Metas Ejecutadas APSB

Este anexo captura la información asociada a la ejecución de recursos requeridos para llevar a cabo las inversiones planeadas, sus posibles fuentes de financiación y demás compromisos y usos que haya identificado la administración municipal para el periodo de gobierno en el sector de APSB. Adicionalmente, se debe registrar la información de la ejecución de las metas de los indicadores de cobertura, calidad, continuidad y aseguramiento en el acceso a agua potable y saneamiento básico.

Para acceder a la herramienta que le permitirá reportar está información, diríjase al módulo **Cargues de información** e ingrese por el submódulo **Metas Ejecutadas APSB** y luego dé clic en la opción **Registrar** (*ver ilustración 20*).

Ilustración 20: Módulo Metas Ejecutadas APSB

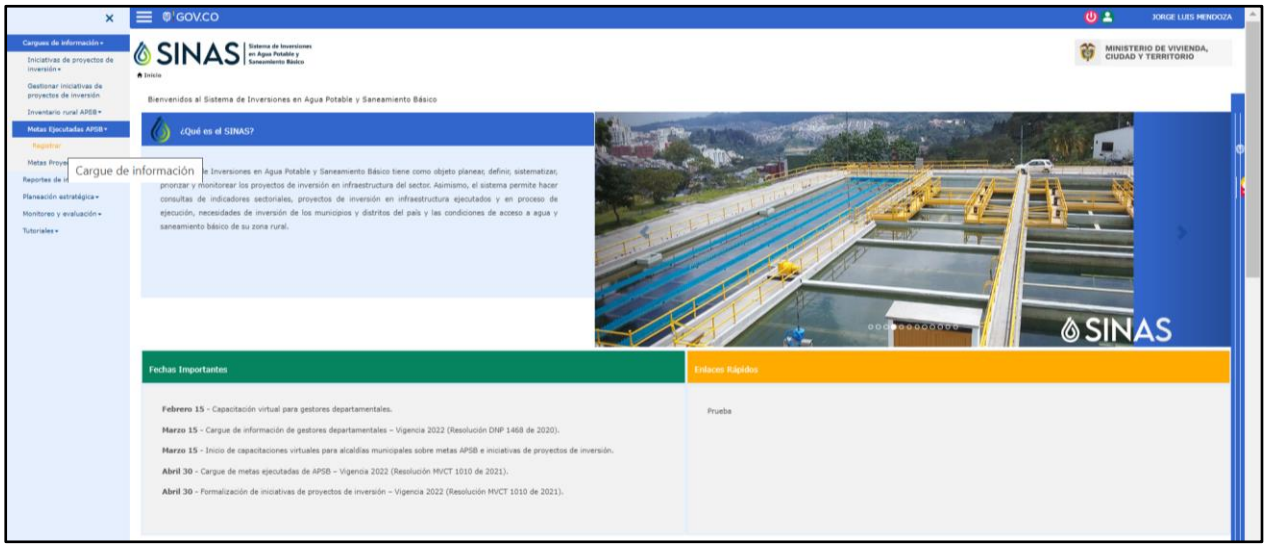

Una vez ingrese al módulo debe descargar para su diligenciamiento la plantilla base que se encuentra en formato Excel, dando clic en el botón "Generar Plantilla" ubicado en el panel lateral derecho del cuadrante medio de la pantalla. El archivo Excel descargado está compuesto por cuatro hojas de cálculo denominadas de la siguiente forma:

- **Plantilla Total Usos.**
- **Plantilla Fuentes.**

- **Plantilla Metas Ejecutadas APSB.**
- **Plantilla Metas Recursos APSB.**

6.2 Descripción y diligenciamiento de las Plantillas

Una vez descargado el archivo se debe diligenciar los campos correspondientes a cada plantilla sin manipular información fuera de ella[4] y teniendo en cuenta las siguientes instrucciones:

6.2.1 Plantilla Total Usos

En la columna A se encuentra precargado el listado de los Compromisos y Usos (*ver ilustración 21*). En la columna B Ingrese el valor por cada compromiso y uso ejecutado en la vigencia a la que corresponde el reporte. Luego debe seleccionar de las listas desplegables en la celda de la columna C, la fuente de financiación correspondiente. Sólo si el compromiso o uso tiene más de una fuente de financiación puede hacer uso de las columnas D y E correspondientesa "Fuente de Financiación 2" y "Fuente de Financiación 3".

Ilustración 21: Plantilla total usos

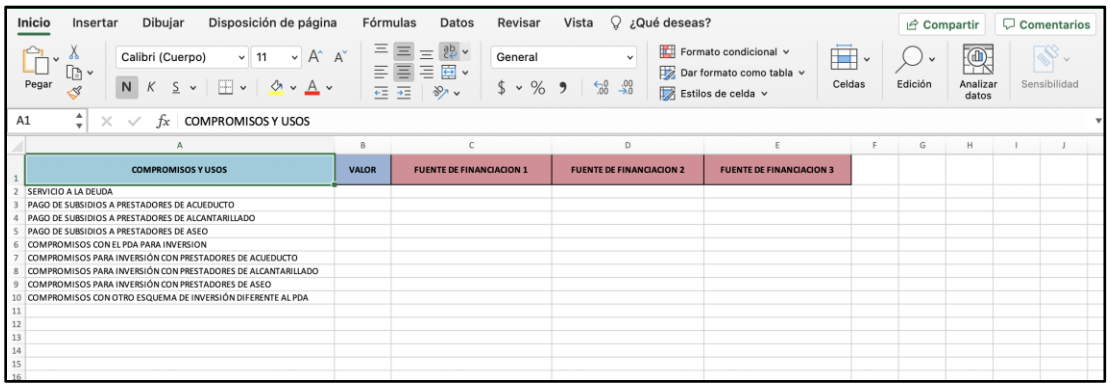

[4] No modifique los textos que ya vienen prediligenciados en las plantillas, ni elimine o adicione filas y columnas de las mismas.

6.2.2 Plantilla Fuentes

En la columna A se encuentra precargados el listado de las fuentes de financiación (*ver ilustración 22*). En la columna B, ingrese el valor para cada fuente de financiación que haya sido ejecutado en la vigencia a la que corresponde el reporte. Para la correcta validación de esta plantilla es obligatorio registrar al menos una fuente de financiación.

Ilustración 22: Plantilla fuentes de financiación

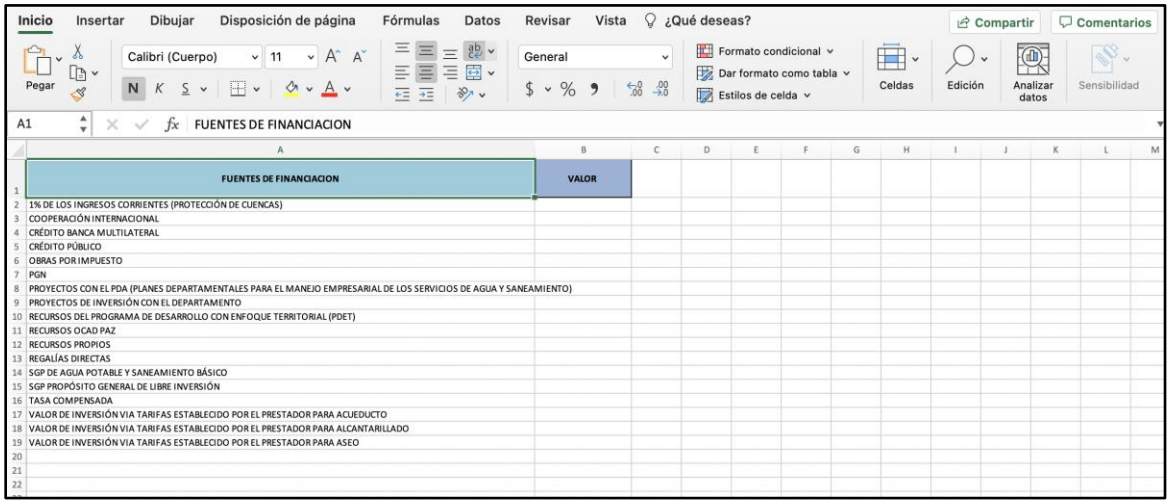

	A	B
1	FUENTES DE FINANCIACION	VALOR
2	1% DE LOS INGRESOS CORRIENTES (PROTECCIÓN DE CUENCAS)	
3	COOPERACIÓN INTERNACIONAL	
4	CRÉDITO BANCA MULTILATERAL	
5	CRÉDITO PÚBLICO	
6	OBRAS POR IMPUESTO	
7	PGN	
8	PROYECTOS CON EL PDA (PLANES DEPARTAMENTALES PARA EL MANEJO EMPRESARIAL DE LOS SERVICIOS DE AGUA Y SANEAMIENTO)	
9	PROYECTOS DE INVERSIÓN CON EL DEPARTAMENTO	
10	RECURSOS DEL PROGRAMA DE DESARROLLO CON ENFOQUE TERRITORIAL (PDET)	
11	RECURSOS OCAD PAZ	
12	RECURSOS PROPIOS	
13	REGALÍAS DIRECTAS	
14	SGP DE AGUA POTABLE Y SANEAMIENTO BÁSICO	
15	SGP PROPÓSITO GENERAL DE LIBRE INVERSIÓN	
16	TASA COMPENSADA	
17	VALOR DE INVERSIÓN VIA TARIFAS ESTABLECIDO POR EL PRESTADOR PARA ACUEDUCTO	
18	VALOR DE INVERSIÓN VIA TARIFAS ESTABLECIDO POR EL PRESTADOR PARA ALCANTARILLADO	
19	VALOR DE INVERSIÓN VIA TARIFAS ESTABLECIDO POR EL PRESTADOR PARA ASEO	

6.2.3 Plantilla Metas Línea Base APSB

Diligencie la Plantilla Metas Ejecutadas APSB, ingresando en las celdas de las columnasde la D a la U, el avance de las metas durante la vigencia a la que corresponde el reporte y en cada uno de los indicadores financiación (*ver ilustración 23*).

Tener en cuenta que los valores a registrar en las columnas N y Q, correspondiente a los indicadores Toneladas Urbanas Dispuestas Sitio de Disposición Final e Índice de Pérdidas por Suscriptor Facturado en la Zona Urbana respectivamente, deben ser diligenciados con números enteros mayor que cero. Para el resto de los indicadores deesta plantilla se deben reportar en valores porcentuales entre 0 y 1, utilizando como separador decimal la coma (,).

Ilustración 23: Metas línea base APSB

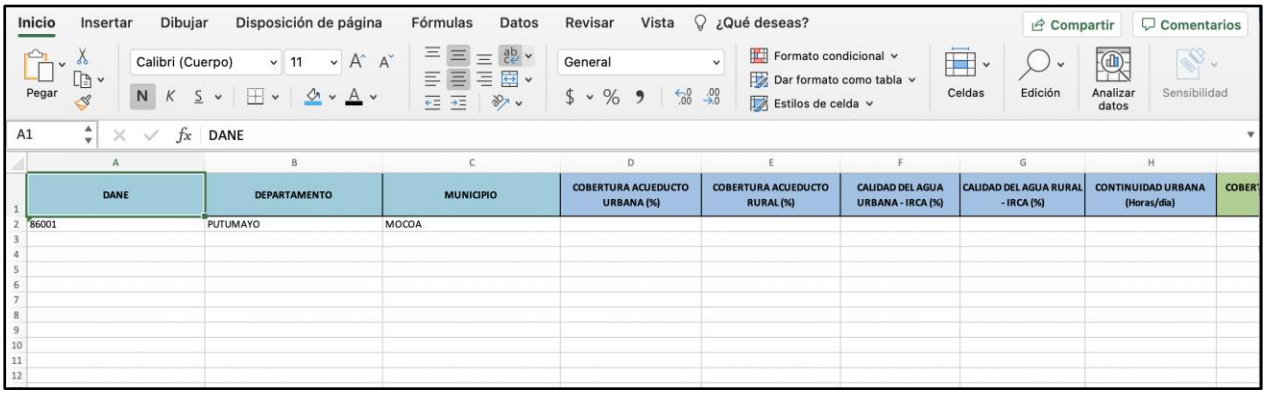

DANE	DEPARTAMENTO	MUNICIPIO	COBERTURA ACUEDUCTO URBANA (%)	COBERTURA ACUEDUCTO RURAL (%)	CALIDAD DEL AGUA URBANA - IRCA (%)	CALIDAD DEL AGUA RURAL - IRCA (%)	CONTINUIDAD URBANA (Horas/día)	COBER
86001	PUTUMAYO	MOCOA						

6.2.4 Plantilla Metas Recursos APSB

Diligencie la Plantilla Metas Recursos APSB, ingresando en la celda de la columna C el monto de los recursos ejecutados durante la vigencia a la que corresponde el reporte, en el cumplimiento de las metas de los indicadores descritosen la columna B (*ver ilustración 24*).

Ilustración 24: Metas recursos APSB

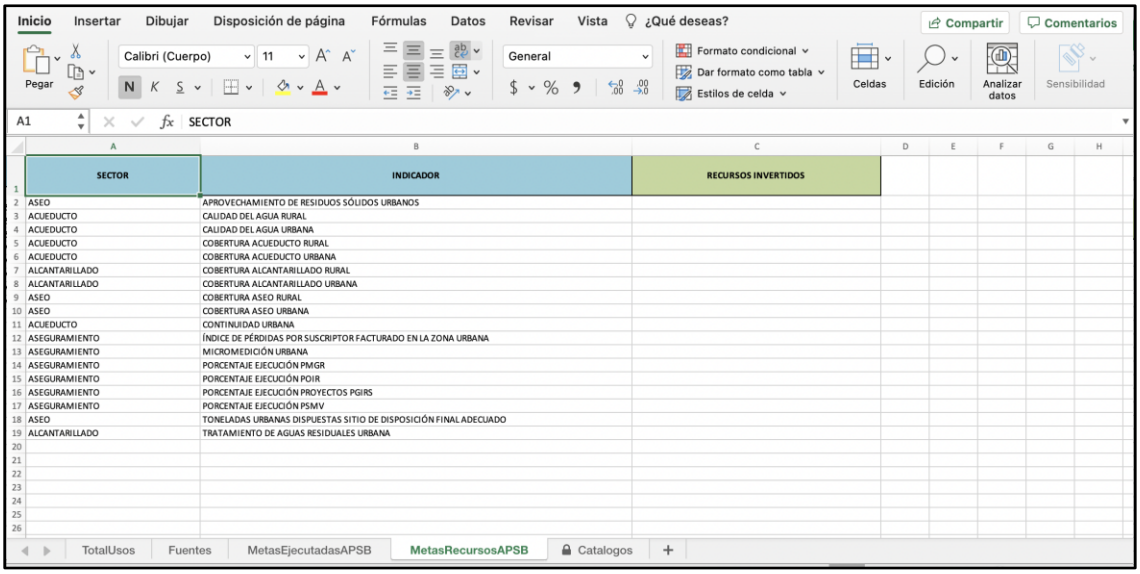

SECTOR	INDICADOR	RECURSOS INVERTIDOS
ASEO	APROVECHAMIENTO DE RESIDUOS SÓLIDOS URBANOS	
ACUEDUCTO	CALIDAD DEL AGUA RURAL	
ACUEDUCTO	CALIDAD DEL AGUA URBANA	
ACUEDUCTO	COBERTURA ACUEDUCTO RURAL	
ACUEDUCTO	COBERTURA ACUEDUCTO URBANA	
ALCANTARILLADO	COBERTURA ALCANTARILLADO RURAL	
ALCANTARILLADO	COBERTURA ALCANTARILLADO URBANA	
ASEO	COBERTURA ASEO RURAL	
ASEO	COBERTURA ASEO URBANA	
ACUEDUCTO	CONTINUIDAD URBANA	
ASEGURAMIENTO	ÍNDICE DE PÉRDIDAS POR SUSCRIPTOR FACTURADO EN LA ZONA URBANA	
ASEGURAMIENTO	MICROMEDICIÓN URBANA	
ASEGURAMIENTO	PORCENTAJE EJECUCIÓN PMGR	
ASEGURAMIENTO	PORCENTAJE EJECUCIÓN POIR	
ASEGURAMIENTO	PORCENTAJE EJECUCIÓN PROYECTOS PGIRS	
ASEGURAMIENTO	PORCENTAJE EJECUCIÓN PSMV	
ASEO	TONELADAS URBANAS DISPUESTAS SITIO DE DISPOSICIÓN FINAL ADECUADO	
ALCANTARILLADO	TRATAMIENTO DE AGUAS RESIDUALES URBANA	

6.3 Diligenciamiento formulario indicadores

Una vez diligenciada la información de las plantillas descargada se procede a cargar dicha información,para esto debe dar clic en el botón "Cargar plantilla" que se encuentra en el panel lateral derecho cuadrante medio del mismo (*ver ilustración 25*).

Ilustración 25: Cargar plantillas

Una vez se da clic en el botón se mostrará el formulario de información referente a los Indicadores cualitativos (*ver ilustración 26*): Tratamiento de Residuos Sólidos Urbanos, Disposición de Residuos Sólidos y Gobierno Corporativo.

Ilustración 26: Formulario indicadores

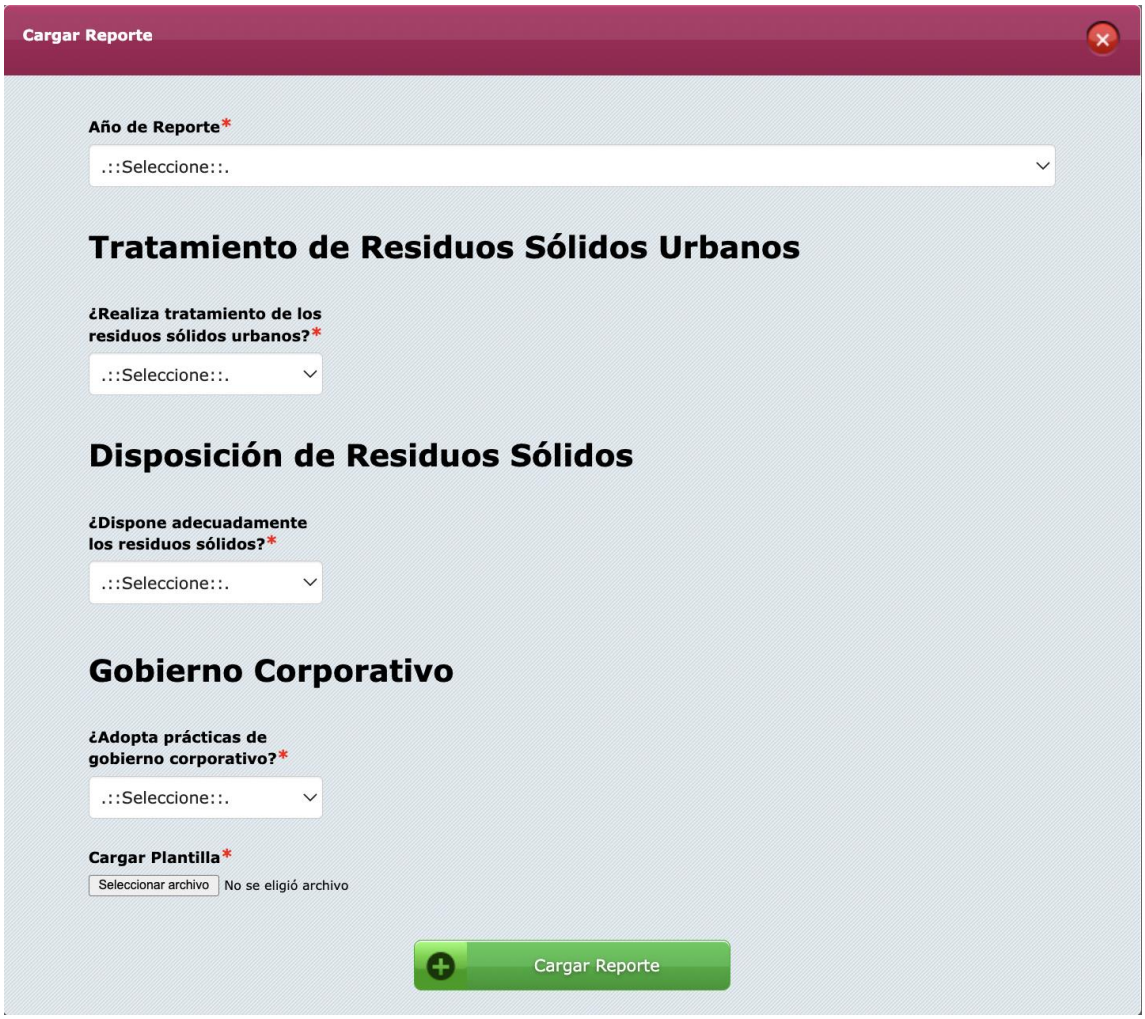

A continuación (*ver ilustración 27*), se describe la forma correcta de diligenciar este formulario:

Ilustración 27: Flujograma formulario indicadores

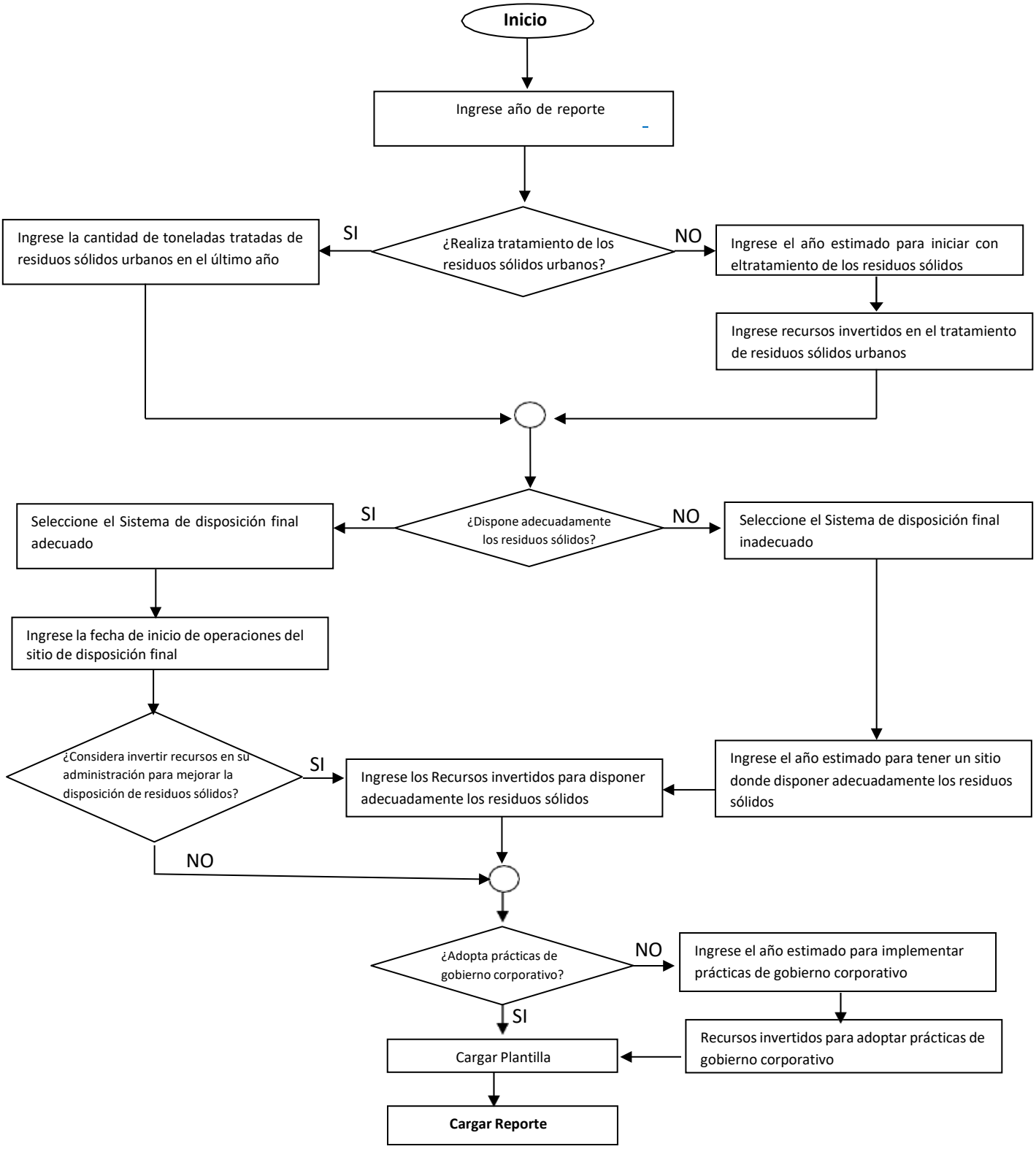

6.4 Cargue de plantillas y validación de información

Como se observa en la Ilustración 24 una vez se diligencia el formulario de indicadores cualitativos se debe proceder a cargar en el sistema el archivo en formato Excel que contiene las plantillas. Para ello se debe dar clic en el botón "Cargar Plantilla" (*ver ilustración 28).*

Ilustración 28: Cargar plantilla

Una vez se dé clic en el botón cargar reporte, el sistema realiza las validaciones correspondientes al archivo antes de realizar la carga de la información. Si el sistema detecta errores mostrará un mensaje informando que no fue posible el cargue de la información, ya que el archivo que se intenta cargar presenta inconsistencias, este mensaje habilita un enlace para la visualización del Log de errores (*ver ilustración 29*).

Ilustración 29: Mensaje log de errores

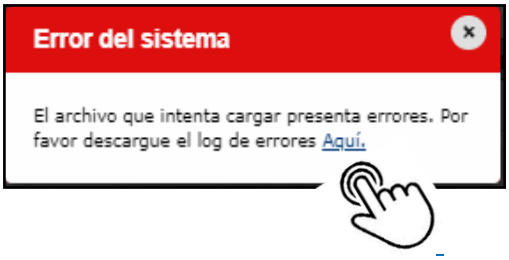

Los errores detectados en el archivo serán identificados fácilmente, ya que la celda se pondrá de color amarillo y esta tendrá un comentario el cual informará la procedencia del error (*ver ilustración 30*).

Ilustración 30: Log de errores identificados

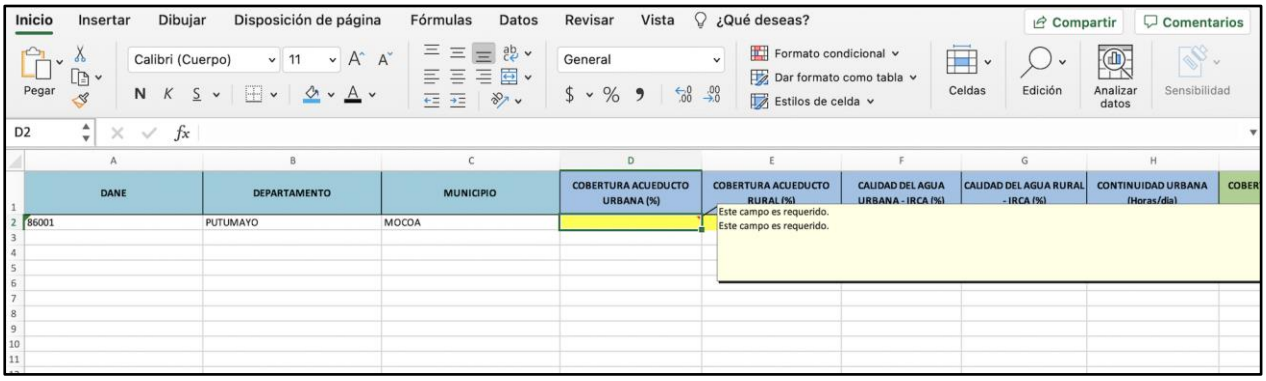

Una vez se corrijan los errores debe proceder a cargar de nuevo el archivo utilizando para ello el icono del lápiz que indica "Actualizar Carga" (*ver ilustración 31*).

Ilustración 31: Actualizar carga

Si el archivo supera las validaciones realizadas por el sistema, se mostrará un mensaje informando quela carga se procesó y se realizó exitosamente, habilitando un enlace para visualizar y descargar el certificado del reporte exitoso (*ver ilustraciones 32 y 33*).

Ilustración 32: Mensaje de validación exitosa

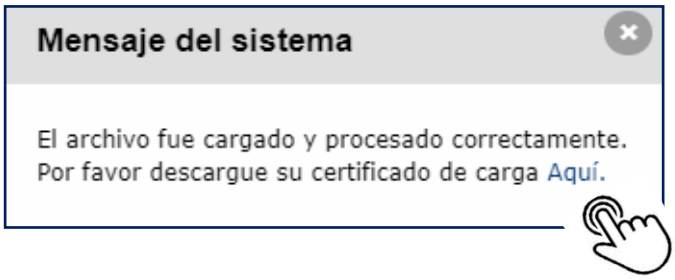

Ilustración 33: Reporte de cargue exitoso

Siglas

APSB	Agua Potable y Saneamiento Básico
CAR	Corporaciones Autónomas Regionales
IRCA	Índice de Riesgo de Calidad del Agua
MVCT	Ministerio de Vivienda, Ciudad y Territorio
OCAD	Órgano Colegiado de Administración y Decisión
PAP-PDA	Programa de Agua para la Prosperidad - Planes Departamentales de Agua
PDET	Programa de Desarrollo con Enfoque en Territorial
PGN	Presupuesto General de la Nación
PGIRS	Plan Gestión Integral de Residuos Sólidos
PMGR	Plan Municipal de Gestión del Riesgo
POIR	Plan de Obras e Inversiones Regulado por el Prestador
PSMV	Plan de Saneamiento y Manejo de Vertimientos
SECOP	Sistema Electrónico de Contratación Pública
SGP	Sistema General de Participaciones
SINAS	Sistema de Inversiones en Agua Potable y Saneamiento Básico
SIVICAP	Sistema de Información de la Vigilancia de la Calidad de Agua para Consumo Humano
SSPD	Superintendencia de Servicios Públicos Domiciliarios